# Modelowanie danych przestrzennych
## Projekt-prezentacja

Andrii Khomenko

Akademia Górniczo-Hutnicza w Krakowie

4 kwietnia 2026

# Analizowany obszar na mapie

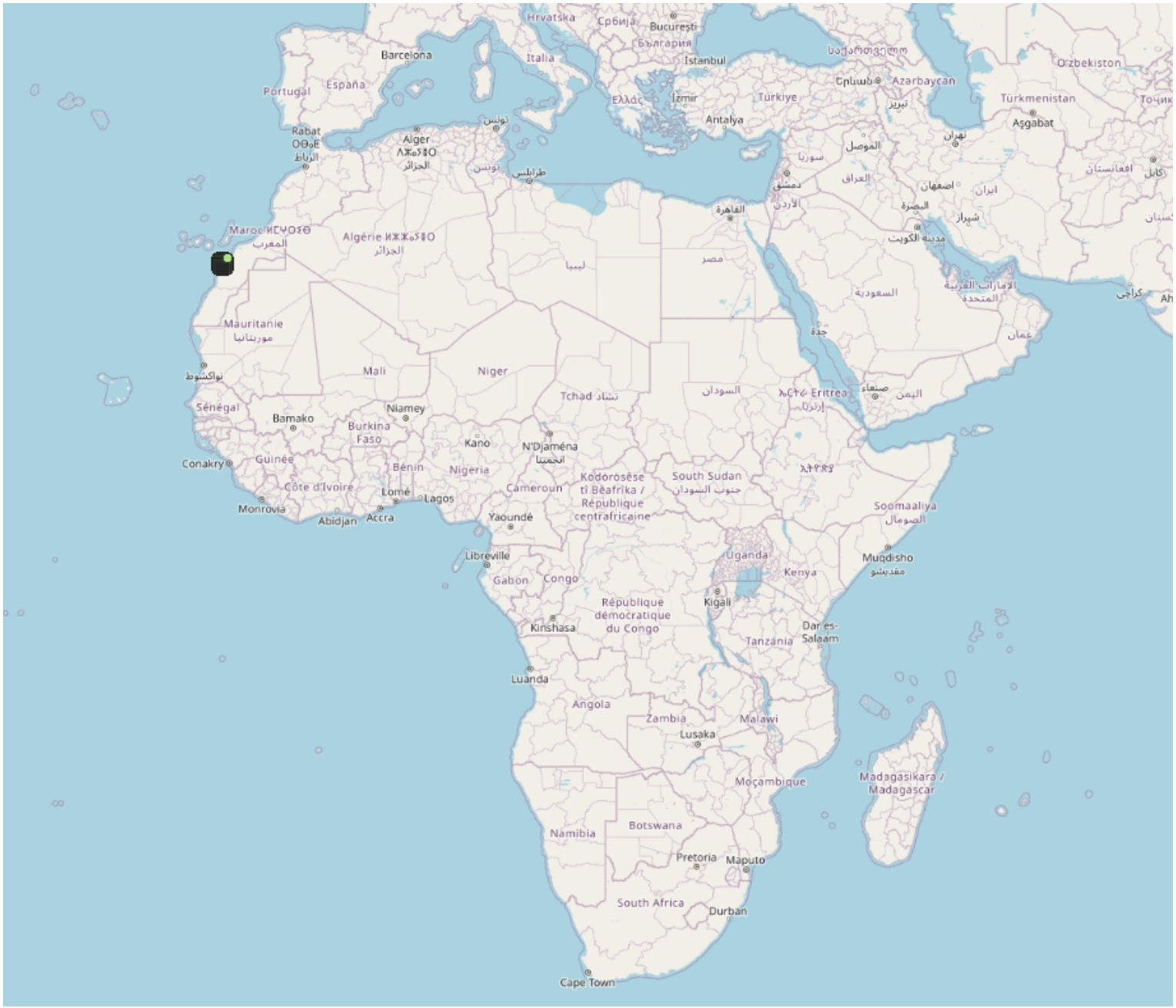

# Informacje podstawowe

Obszar badań zlokalizowany jest u wybrzeży północno-zachodniej Afryki, w obrębie wschodniej części Oceanu Atlantyckiego, w sąsiedztwie wybrzeża Maroka i Sahary Zachodniej. Analizowany teren obejmuje zarówno fragment obszaru lądowego, jak i przyległą strefę morską, co umożliwia jednoczesną analizę rzeźby terenu oraz batymetrii dna morskiego.

Zakres wartości wysokościowych w badanym obszarze wynosi od około **+122 m** do **-2750 m**, co wskazuje na obecność stromych spadków batymetrycznych oraz wyraźne zróżnicowanie morfologiczne.

**Źródła:**

- OpenStreetMap

# Mapa interpolacji TIN wykonana w QGIS

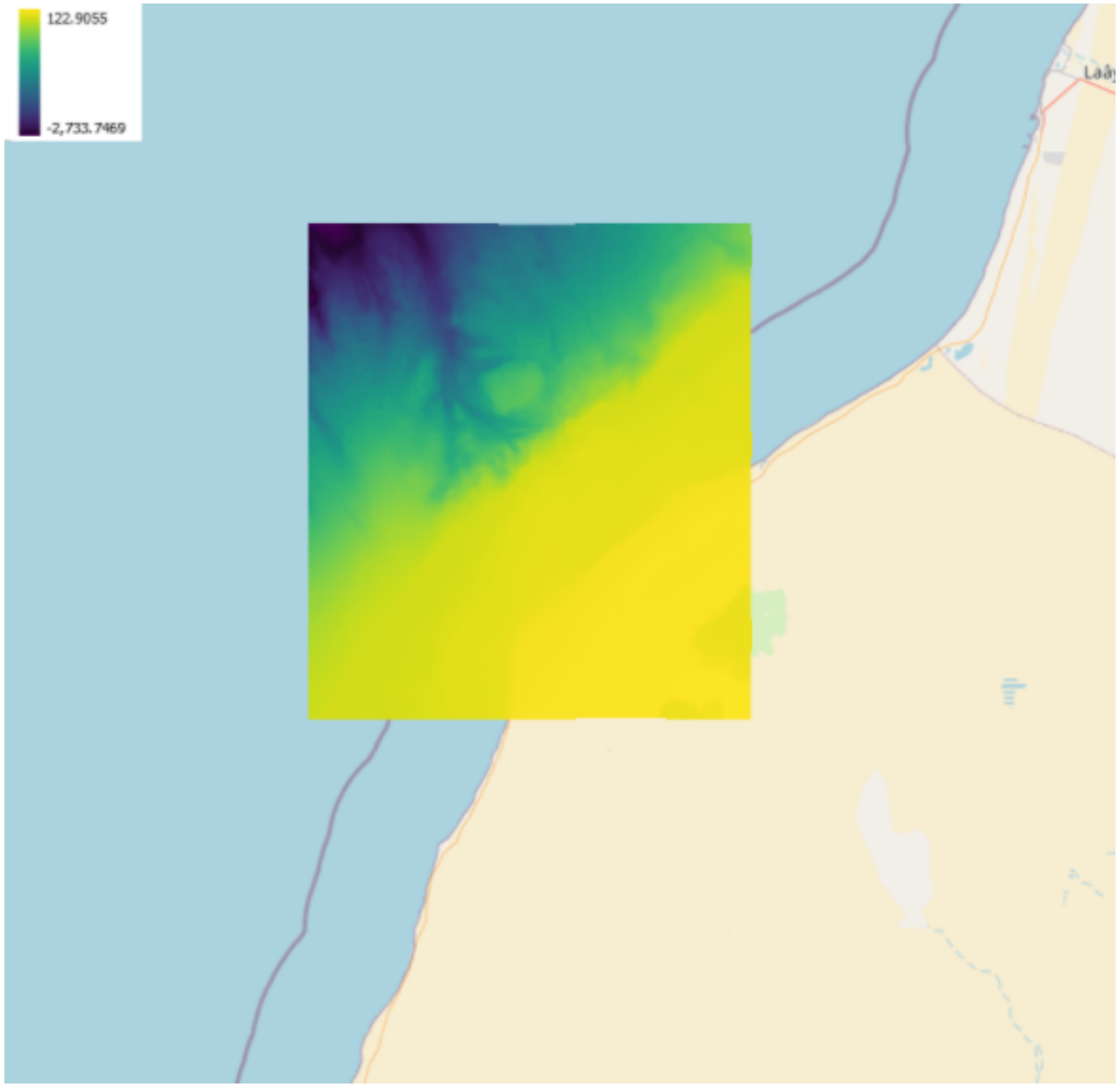

# Mapa azymutów (QGIS)

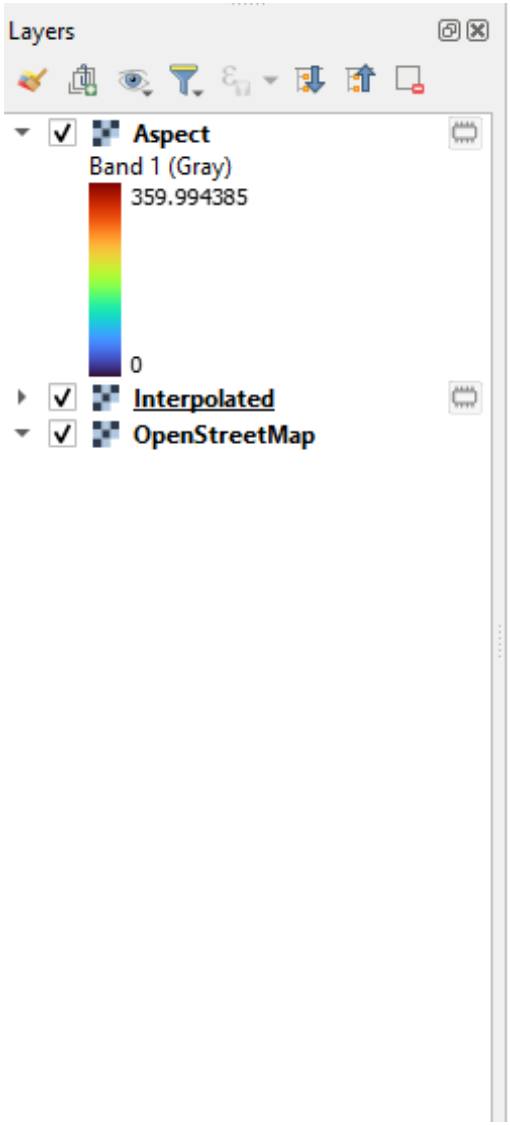




# Mapa azymutów (ParaView)

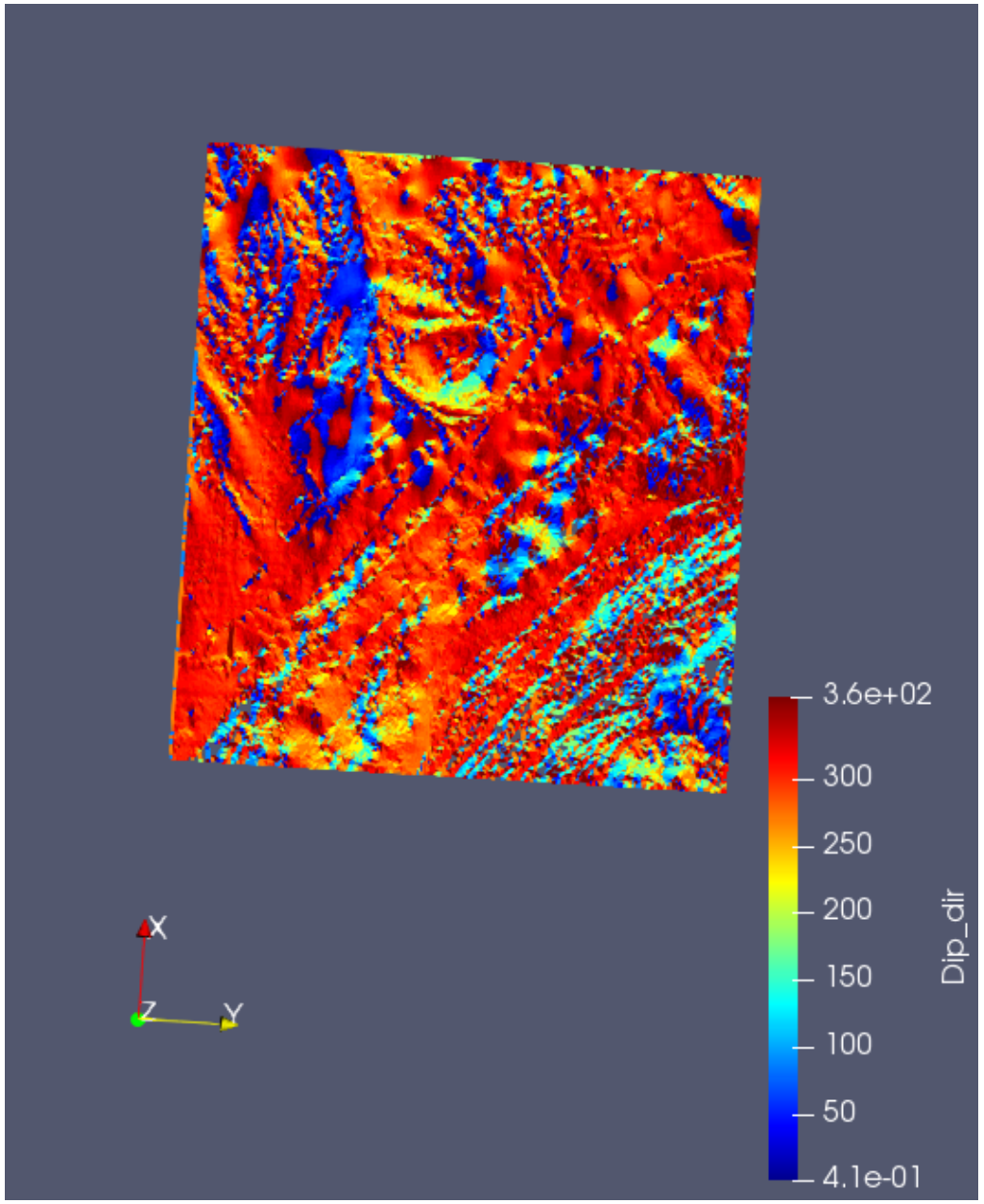

# Grupowanie orientacji powierzchni

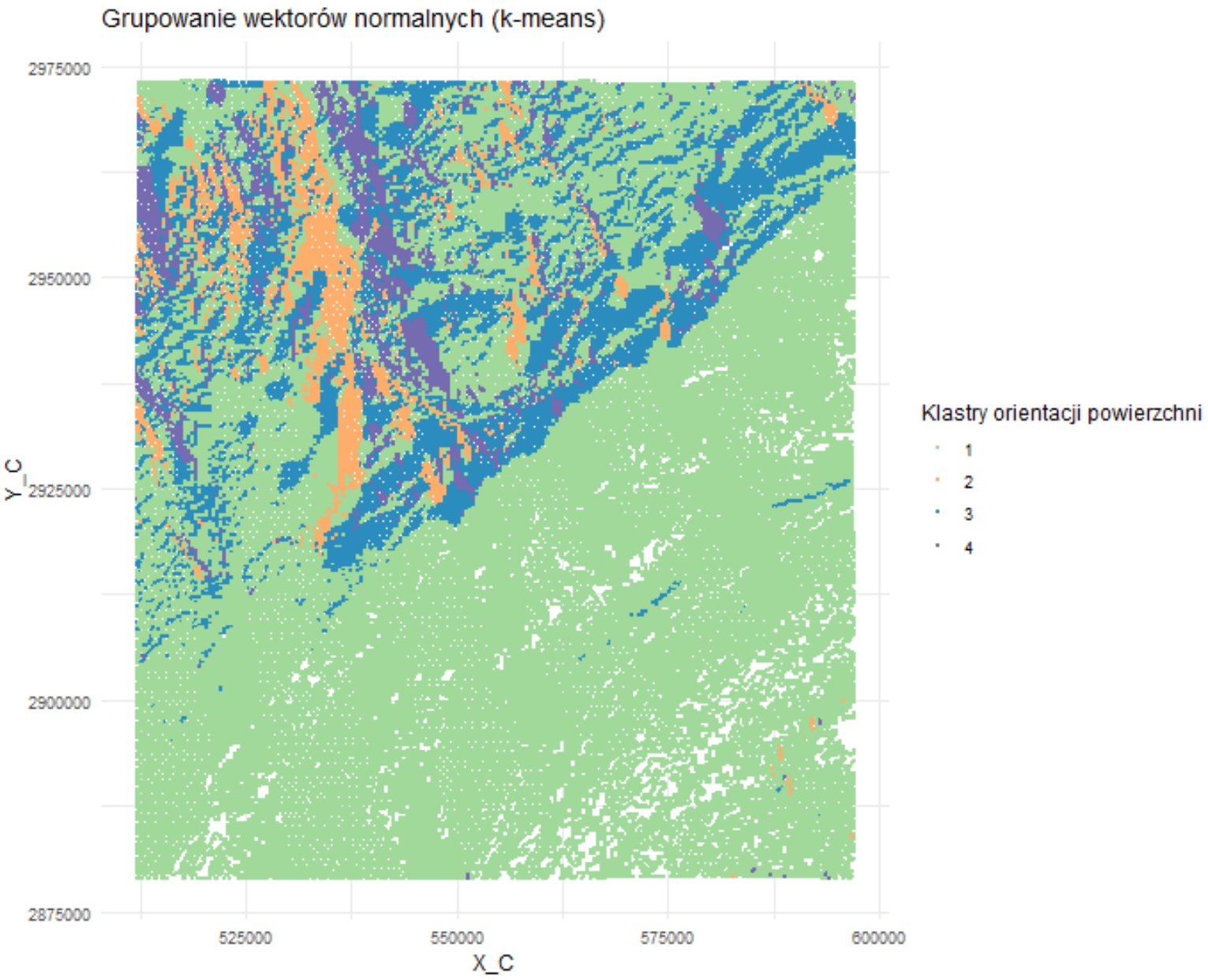

# Stereonet - orientacja powierzchni

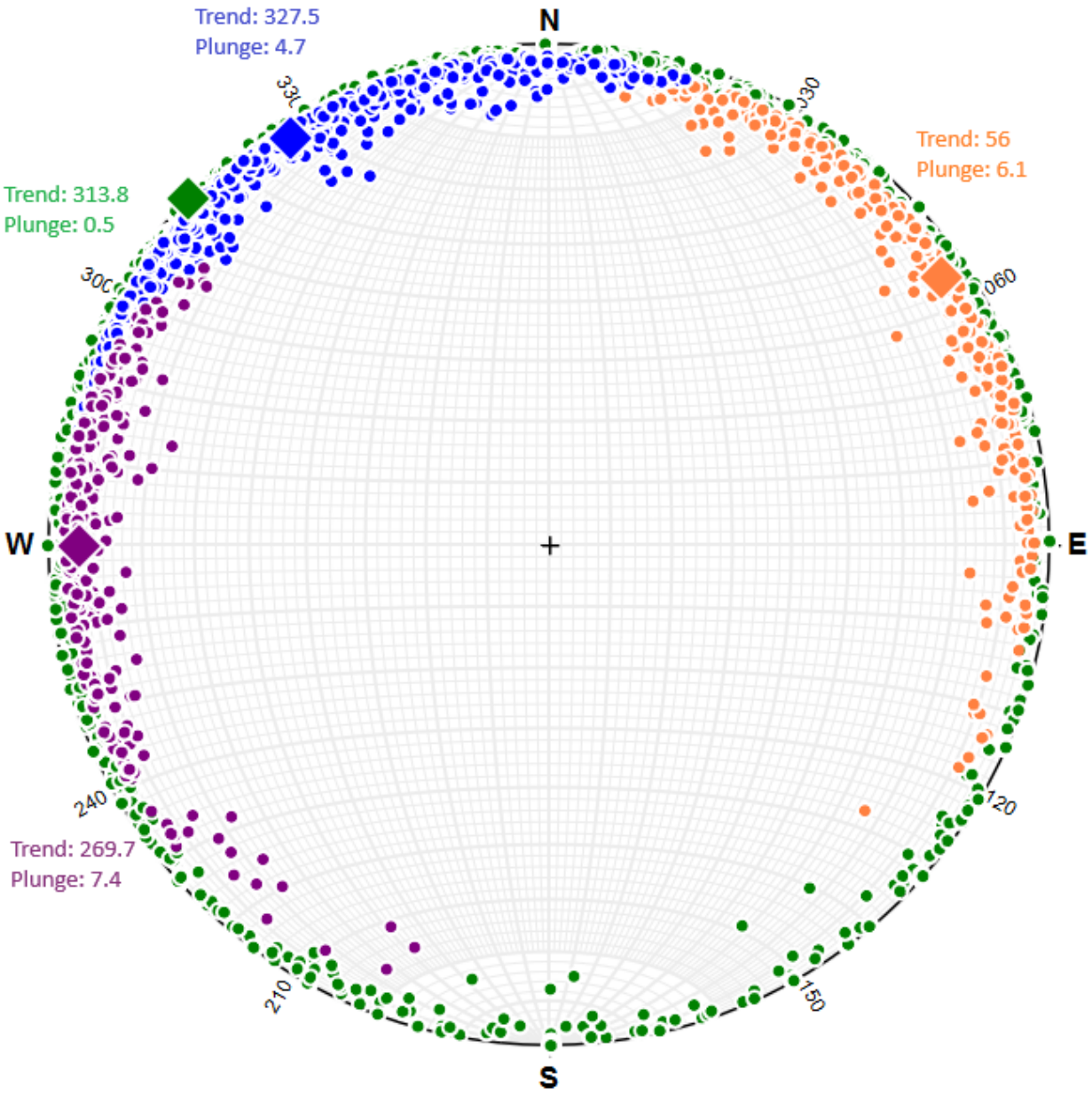

# Grupowanie kierunków spadku

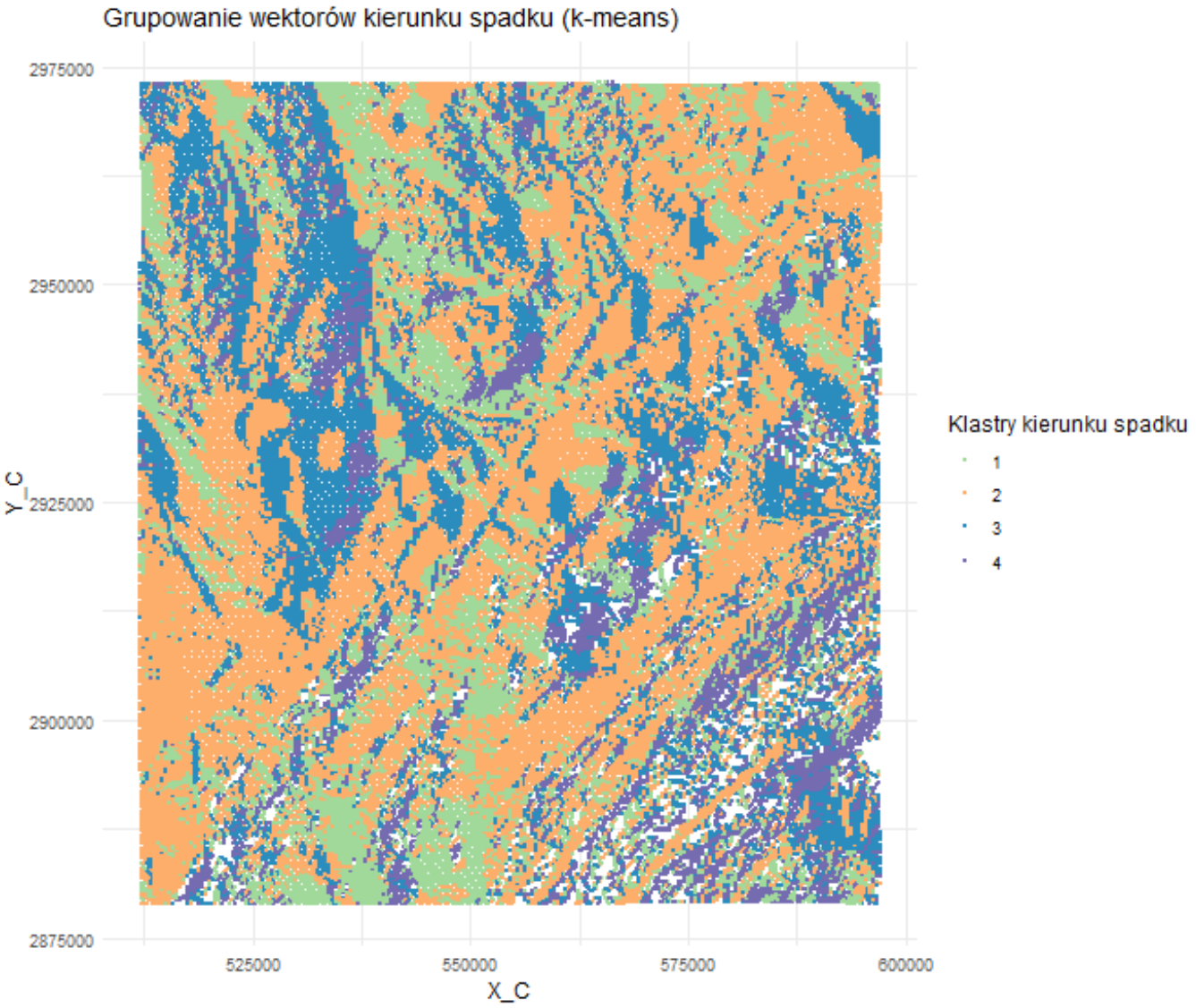

# Stereonet - kierunki spadku

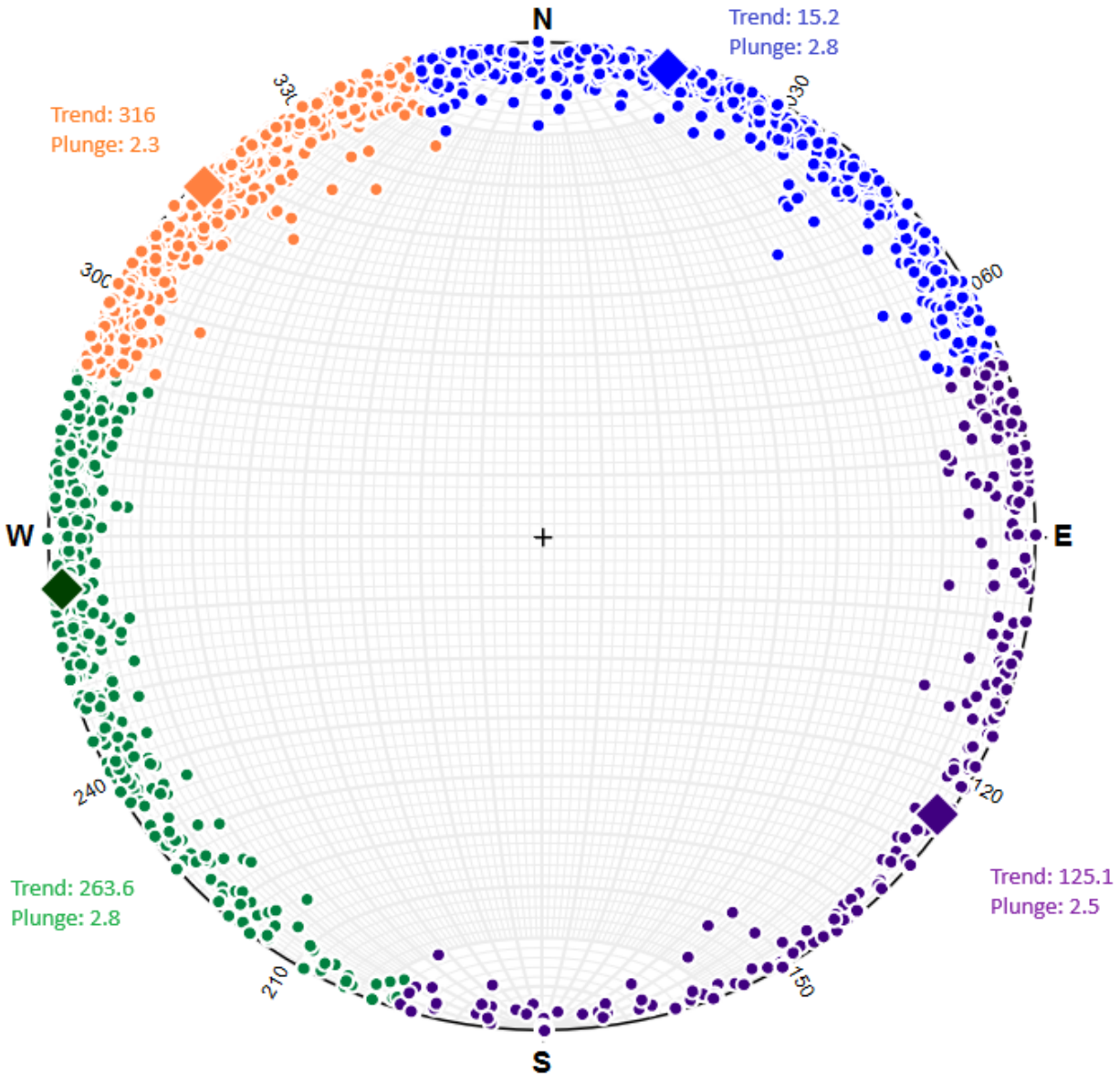
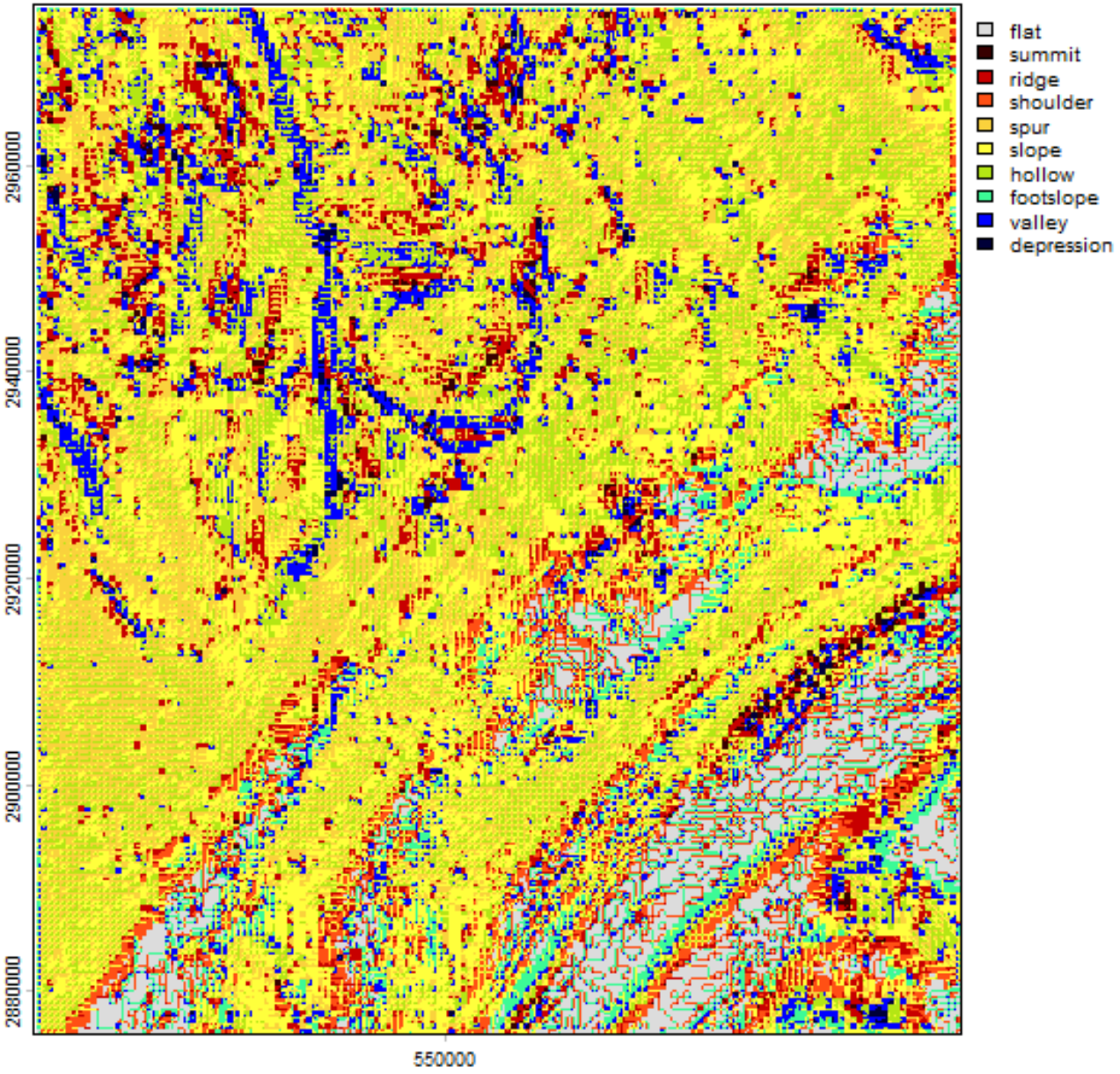
# Mapa Geomorfonów